Stadt Liebstadt

Vorhabenbezogener Bebauungsplan „Solarpark Waltersdorf“

Planteil A: Zeichnerische Festsetzungen
Planteil B: Textliche Festsetzungen

Planungsstand	**E N T W U R F**
Planfassung	19.12.2025
Stadt	Liebstadt
Vorhabenträger	SOLARPARK WALTERSDORF GMBH & CO.KG Waltersdorfer Str. 1 01825 Liebstadt
Auftragnehmer	LANDSCHAFTSARCHITEKTUR PANSE GBR Martin-Hoop-Str.12, 02625 Bautzen Tel.: 03591/52930, Fax: 03591/529329

Planteil A - Zeichnerische Festsetzungen

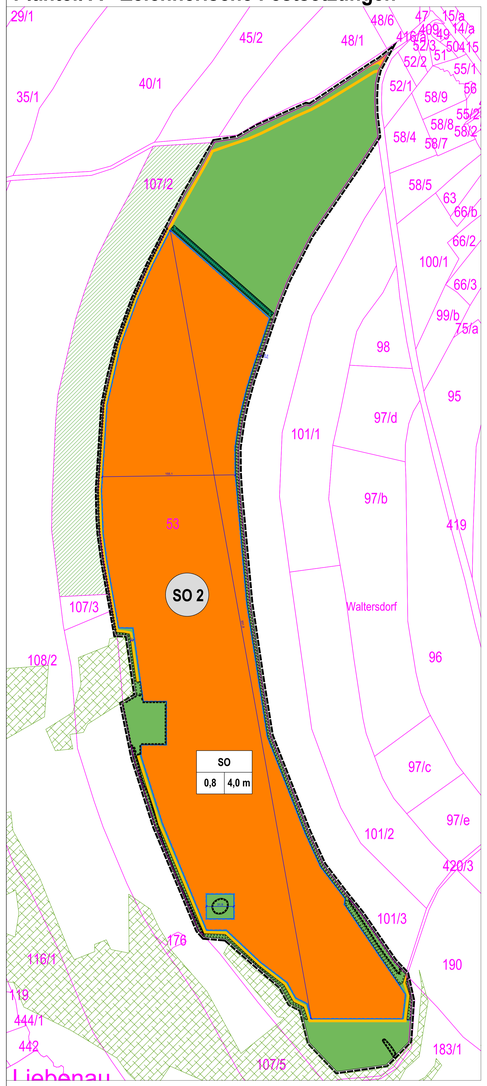

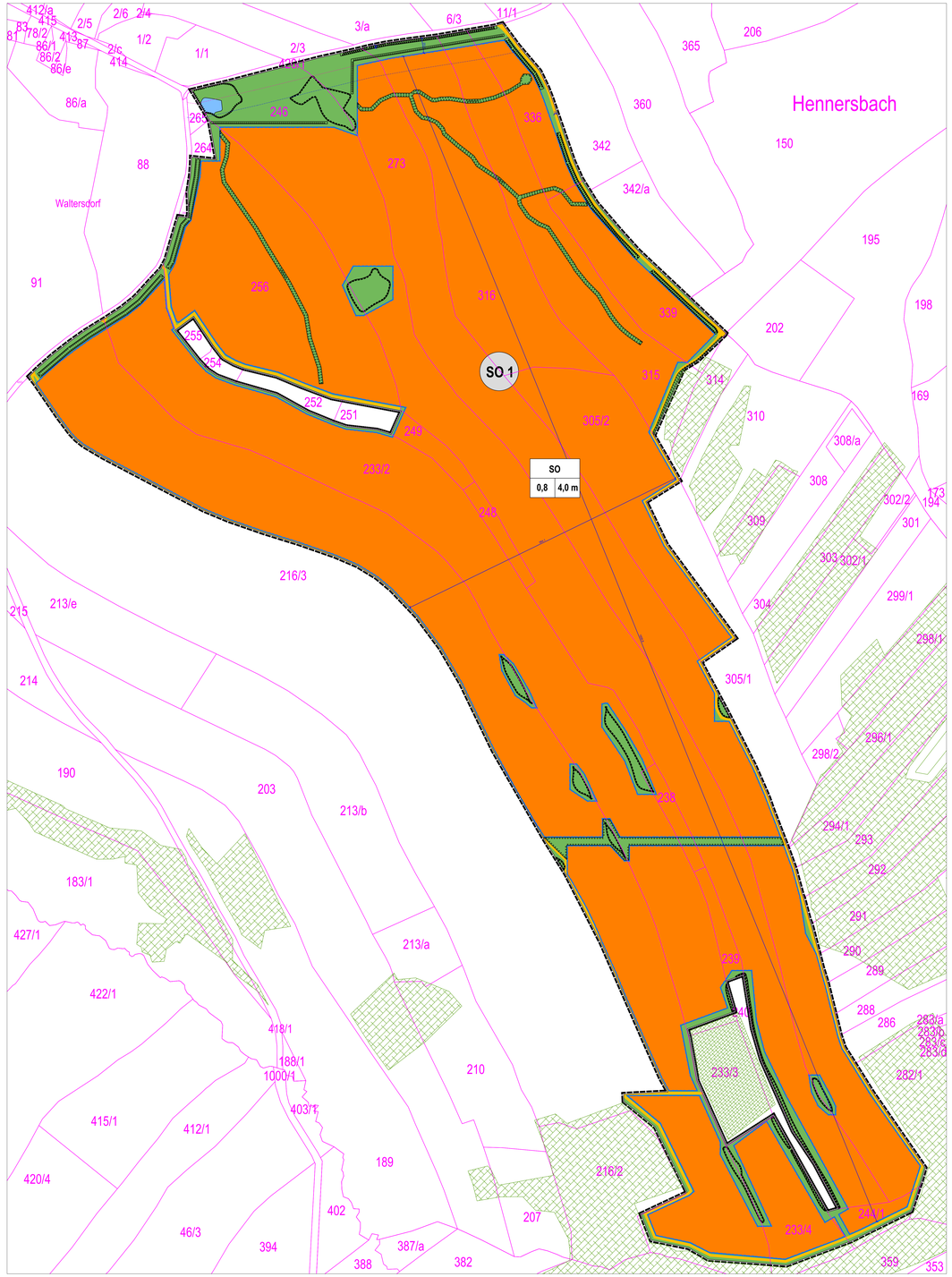

Kartengrundlage: Lage- und Höhenplan Vermessungsbüro Hering , 2025

Kompensationsmaßnahmen außerhalb des Geltungsbereichs in der Gemarkung Döbra (TF 365 und TF 371) zur Deckung des Kompensationsbedarfes des vB-Plans "Solarpark Waltersdorf"

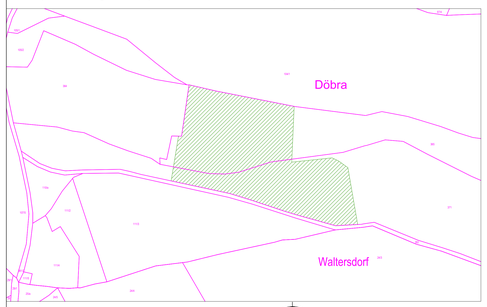

Planzeichenerklärung

Art der baulichen Nutzung
(§ 9 Abs.1 Nr.1 des Baugesetzbuches - BauGB,
§§ 1 bis 11 der Baunutzungsverordnung - BauNVO)

- Sonstige Sondergebiete (§ 11 BauNVO)

Bauweise, Baulinien, Baugrenzen
(§ 9 Abs.1 Nr.2 BauGB, § 22 und 23 BauNVO)

- Baugrenze

Verkehrsflächen
(§ 9 Abs.1 Nr.11 und Abs.6 BauGB)

- Interner Erschließungsweg

Grünflächen
(§ 9 Abs.1 Nr.15 und Abs.6 BauGB)

- private Grünfläche, Zweckbestimmung: Erhalt / Ausgleichsflächen

Wasserflächen und Flächen für die Wasserwirtschaft, den Hochwasserschutz und die Regelung des Wasserabflusses
(§ 9 Abs.1 Nr.16 und Abs.4 BauGB)

- Wasserflächen

Planungen, Nutzungsregelungen, Maßnahmen und Flächen für Maßnahmen zum Schutz, zur Pflege und zur Entwicklung von Natur und Landschaft
(§ 9 Abs.1 Nr.20, 25 und Abs.6 BauGB)

- Umgrenzung von Flächen für Maßnahmen zum Schutz, zur Pflege und Entwicklung von Natur und Landschaft (§ 9 Abs.1 Nr.20 und Abs.6 BauGB)
- Umgrenzung von Flächen zum Anpflanzen von Bäumen, Sträuchern und sonstigen Bepflanzungen (§ 9 Abs.1 Nr.25a und Abs.6 BauGB)
- Umgrenzung von Flächen mit Bindungen für Bepflanzungen und für die Erhaltung von Bäumen, Sträuchern und sonstigen Bepflanzungen, sowie von Gewässern (§ 9 Abs.1 Nr.25b und Abs.6 BauGB)
- Umgrenzung von Schutzgebieten und Schutzobjekten im Sinne des Naturschutzrechtes (§ 9 Abs.6 BauGB und § 22 BNatSchG)

Sonstige Planzeichen

- Grenze des räumlichen Geltungsbereiches (§ 9 Abs.7 BauGB)

Kompensationsmaßnahmen außerhalb des Geltungsbereichs

- Ausgleichsflächen

SO	Art der baulichen Nutzung
0,8 / 4,0 m	GRZ / Oberkante

Darstellung ohne Normcharakter

- 13/a Flurstücksgrenze und Flurstücksnummer
- Gemarkungsgrenze und Gemarkungsname
- 22,0 Bemaßung (Meter)

Nachrichtliche Übernahme

- Anbauverbotszone Kreisstraße 20 m
- Anbaubeschränkungszone Kreisstraße 40 m
- Wald nach sächs. Waldgesetz

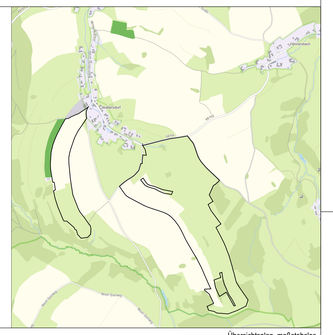

Übersichtsplan, maßstabslos

Planteil B - Textliche Festsetzungen

Bauplanungsrechtliche Festsetzungen (§ 9 Abs. 1 Nr. 1 BauGB und §§ 2-21aBauNVO)

Art der baulichen Nutzung

1. Gemäß §11 Abs. 2 BauNVO ist in den beiden Sonstigen Sondergebieten (SO 1 und SO 2) die Errichtung von photovoltaischen Freiflächenanlagen einschließlich der zur Betreibung erforderlichen Trafostationen, Umspannstationen, Wechselrichterstationen, Stromspeicher (technische Nebenanlagen), Wege und Zaunanlagen zulässig.

Maß der baulichen Nutzung

2. Die maximale Höhe baulicher Anlagen gemäß §18 BauNVO wird auf 4,00 m über der vorhandenen gewachsenen Geländeoberfläche festgesetzt. Für technische Anlagen zum Betrieb und zur Überwachung ist eine Überschreitung der festgesetzten Maximalhöhe bis 8,00 m zulässig.

Verkehrsflächen (§ 9 Abs. 1 Nr. 11 BauGB)

3. Zur Gewährleistung des Zugangs zu den Flurstücken 233/3 und 240, Gemarkung Waltersdorf sowie zu den Flurstücken 251, 252, 254 und 255, Gemarkung Waltersdorf ist ein mindestens 3,00 m breiter interner Erschließungsweg dauerhaft freizuhalten. Dieser Erschließungsweg muss jederzeit für Fußgänger begehbar und für Fahrzeuge (z. B. PKW, Traktoren und Forsttechnik, Feuerwehr) befahrbar sein. Eine Einschränkung oder Blockierung dieser Zuwegung durch bauliche Anlagen, Zaunanlagen, Vegetation oder andere Hindernisse ist unzulässig.
4. Die Befestigung von Zufahrten und sonstigen Wegen ist wasserdurchlässig auszuführen (z. B. Schotterrasen, Rasengitter, Mineralgemisch, wassergebundene Wegedecke).

Flächen für besondere Anlagen und Vorkehrungen zum Schutz vor schädlichen Umwelteinwirkungen im Sinne des Bundes-Immissionsschutzgesetzes (§ 9 Abs. 1 Nr. 24 BauGB)

5. Zum Schutz der Verkehrsteilnehmer sowie schutzwürdiger Räume vor optischen Immissionen darf von den Modulen keine Blendwirkung ausgehen. Die Module müssen so ausgerichtet, dass Blendwirkungen auf angrenzende Wohngebäude ausgeschlossen sind.
6. Technische Nebenanlagen, von denen Geräusche emittiert werden (z. B. Stromspeicher, Trafostationen etc.), sind im Geltungsbereich so anzuordnen, dass der Betrieb dieser nicht zu erheblichen Lärmimmissionen an schutzbedürftigen Nutzungen führen kann.

Löschwasser

7. Es sind Löschwasserentnahmestellen mit einer gesamten Löschwasserkapazität von 400 l/min zu schaffen. Die Löschwassermenge muss über mind. 2 Stunden zur Verfügung stehen.

Bauordnungsrechtliche Festsetzungen (§89 SächsBO)

Einfriedungen

8. Einfriedungen sind mit einer Höhe von max. 3,00 m über Gelände inklusive Übersteigschutz zulässig. Die Einfriedungen sind ohne Sockelmauern herzustellen. Der Abstand zwischen Boden und neu zu errichtenden Einfriedungen muss mind. 0,10 m bis max. 0,20 m betragen. An der Einfriedung ist die Montage von Blendschutz- und Sichtschutzvorrichtungen zulässig. Zusätzliche Wilddurchlässe in Ost-West-Ausrichtung sind in Form eines Verzichtes auf Einzäunung oder als alternative Abgrenzung mit natürlichen Materialien umzusetzen.

Werbeanlagen

9. Werbeanlagen sind nur zulässig, wenn deren Inhalt mit der Photovoltaikanlage in unmittelbarem Zusammenhang steht. Sie dürfen 2,50 m² nicht überschreiten.

Grünordnerische Festsetzungen (§ 9 Abs. 1, 1a BauGB)

Vermeidungs- und Verminderungsmaßnahmen
Durchführung von Bodenarbeiten

10. Durchführung der Bodenarbeiten (Verankerung der Module, Einbringen von Leitungen) in den Offenlandbereichen sind vom 1. Oktober bis 28. Februar außerhalb der Brutzeit von Vögeln zulässig. Ist die Einhaltung des genannten Zeitraumes nicht möglich, muss die ökologische Baubegleitung (CEF 2) Maßnahmen einleiten, die eine Schädigung geschützter Tierarten vermeiden.

Verzicht auf nächtliche Bauaktivitäten

11. Auf nächtliche Bauaktivitäten zur Vermeidung baubedingter Störungen von dämmerungs- und nachtaktiven Tierarten (z. B. Fledermäuse) ist zu verzichten.

Niederschlagswasser (§ 9 Abs. 1 Nr. 20 BauGB)

12. Das im Plangebiet anfallende Niederschlagswasser ist ungesammelt, breitflächig zu versickern. Die Module sind untereinander mit einem Abstand > 1 cm zu montieren.

Beschränkung Sicherungsmaßnahmen:

13. Für die Bewachung der Anlage dürfen keine freilaufenden Hunde eingesetzt werden, eine dauerhafte Beleuchtung der Anlage muss unterbleiben.

Verzicht auf Hilfsstoffe

14. Dünge- und Pflanzenschutzmittel sowie nicht biologisch abbaubare Reinigungsmittel sind unzulässig.

Gehölzentfernung

15. Eine etwaige Fällung von Einzelbäumen ist gem. § 39 Abs. 5 BNatSchG außerhalb der Brutzeit von Vögeln zwischen dem 1. Oktober und 28. Februar vorzunehmen.

Flächen oder Maßnahmen zum Schutz, zur Pflege und zur Entwicklung von Natur und Landschaft (§9 (1) Nr. 20 BauGB)

15. Die in den Maßnahmenblättern M1 – M2 (Anlage 1-I zum Entwurf, Stand: 19.12.2025) konkretisierten Maßnahmen zum Schutz, zur Pflege und zur Entwicklung von Natur und Landschaft sind verbindlich umzusetzen.
16. Für die in der Planzeichnung gemäß § 9 Abs. 1 Nr. 20 BauGB festgesetzten Flächen sind die in den Maßnahmenblättern M3 – M9 (Anlage 1-I-II zum Entwurf, Stand 19.12.2025) konkretisierten Maßnahmen verbindlich umzusetzen.
17. Art, Umfang und Lage der Maßnahmen ergeben sich aus den genannten Maßnahmenblättern. Abweichungen sind nur zulässig, wenn sie nach Abstimmung mit der Unteren Naturschutzbehörde gleichwertig sind.

Flächen für das Anpflanzen von Bäumen, Sträuchern und sonstigen Bepflanzungen (§ 9 Abs. 1 Nr. 25a BauGB)

18. Für die in der Planzeichnung gemäß § 9 Abs. 1 Nr. 25a BauGB festgesetzten Flächen sind die in den Maßnahmenblättern M10 – M11 (Anlagen 1–III zum Entwurf, Stand: 19.12.2025) konkretisierten Maßnahmen verbindlich umzusetzen.
19. Art, Umfang und Lage der Maßnahmen ergeben sich aus den genannten Maßnahmenblättern. Abweichungen sind nur zulässig, wenn sie nach Abstimmung mit der Unteren Naturschutzbehörde gleichwertig sind.

Bindungen für die Erhaltung von Bäumen, Sträuchern und sonstigen Bepflanzungen sowie von Gewässern (§ 9 Abs. 1 Nr. 25b BauGB)

20. Die vorhandenen Steinrücken und Feldgehölze im Geltungsbereich sind als Bestandteil des Biotopverbundsystems gemäß § 20 BNatSchG und § 22 SächsNatSchG in ihrer Funktion als Trittstein- und Verbindungselemente dauerhaft zu sichern. Es ist ein mindestens 5,00 m breiter Pufferbereich freizuhalten. In diesem Bereich sind bauliche Anlagen, Materiallagerungen sowie Bodeneingriffe während der Bauphase und des Betriebs der Anlage unzulässig.
21. Während der Durchführung der Baumaßnahmen sind die Gehölze gemäß DIN 18920 wirksam zu schützen. Sie sind während der Bauphase vor Befahrung, Fällung, Rückschnittmaßnahmen, Ablagerungen und sonstiger Nutzung zu bewahren. Im Falle eines durch Baumaßnahmen verursachten Verlustes sind die Gehölze durch eine Neupflanzung standortgerechter heimischer Arten in der folgenden Pflanzperiode gleichwertig zu ersetzen.

Nachrichtliche Übernahme nach dem BNatSchG

Schutzgebiete

Der Geltungsbereich liegt innerhalb des Landschaftsschutzgebiets (LSG) „Unteres Osterzgebirge".

Hinweise

Natur- und Artenschutz

Realisierungen von Vorhaben sind nur zulässig, wenn sichergestellt ist, dass die Zugriffsverbote der §§ 39 und 44 BNatSchG nicht eintreffen werden.

Für die Umsetzung der erforderlichen externen Maßnahmen zum Artenschutz sind außerhalb des Geltungsbereichs Flächen dinglich zu sichern. Dies betrifft für die CEF-Maßnahme aus Maßnahmenblatt M8 ca. 3,1 ha auf dem Flurstück 107/2 in der Gemarkung Waltersdorf sowie für die CEF-Maßnahme aus Maßnahmenblatt M9 ca. 2 ha auf den Flurstücken 365 und 371 in der Gemarkung Döbra (Anlage 1–II zum Entwurf, Stand: 19.12.2025).

Forstbaumarten müssen aus autochthoner Anzucht des Vorkommensgebiets III „Südostdeutsches Hügel- und Bergland" (VKG 3) stammen. Die Pflanzenqualität muss den Gütebestimmungen für Baumschulpflanzen der Forschungsgesellschaft Landschaftsentwicklung-Landschaftsbau e. V. entsprechen.

Gemäß § 40 BNatSchG ist bei der Verwendung von zertifizierten Regio-Saatgut darauf zu achten, dass es aus dem Ursprungsgebiet UG 08 – „Erz- und Elbsandsteingebirge" stammt. Das Ausbringen von Arten aus angrenzenden Ursprungsgebieten bedarf einer Ausnahmegenehmigung der Unteren Naturschutzbehörde.

Verfahrensvermerke

1. Die Stadtversammlung der Stadt Liebstadt hat mit Beschluss vom..... den vorhabenbezogenen Bebauungsplan "Solarpark Waltersdorf" gem. § 10 Abs. 1 BauGB in der Fassung vom ..... als Satzung beschlossen.

   Stadt Liebstadt, den ....
   Bürgermeister

2. Der Satzungsbeschluss wurde am ..... durch.....bekannt gemacht.

   Stadt Liebstadt, den ....
   Bürgermeister

3. Der vorhabenbezogene Bebauungsplan einschließlich der Begründung wird hiermit ausgefertigt. Es wird hiermit bestätigt, dass die Planurkunde öffentlich ausgelegen hat und von der Stadtversammlung als Satzung beschlossen worden ist.

   Stadt Liebstadt, den ....
   Bürgermeister

4. Vermessungs- und katasterrechtliche Bescheinigung
   Die verwendete Planunterlage enthält den Inhalt des Liegenschaftskatasters und weist die Planrelevanten baulichen Anlagen sowie Straßen, Wege und Plätze vollständig nach. Sie ist hinsichtlich der planungsrelevanten Bestandteile geometrisch einwandfrei. Die Übertragbarkeit der neu zu bildenden Grenzen in die Örtlichkeit ist einwandfrei möglich.

   ....., den .....
   Öffentlich bestellter Vermessungsingenieur

Rechtsgrundlage

Bundesrecht

- **BauGB**
  Baugesetzbuch in der Fassung der Bekanntmachung vom 3. November 2017 (BGBl.I S. 3634),das zuletzt durch Artikel des Gesetzes vom 20. Dezember 2023 (BGBl. 2023 I Nr. 394) geändert worden ist
- **BauNVO**
  Baunutzungsverordnung in der Fassung der Bekanntmachung vom 21. November 2017 (BGBl.I S. 3786), die zuletzt durch Artikel 2 des Gesetzes vom 3. Juli 2023 (BGBl. 2023 I Nr. 176) geändert worden ist
- **PlanZV**
  Planzeichenverordnung vom 18.Dezember 1190 (BGBl.I 1191 I S. 58), die zuletzt durch Artikel 3 des Gesetzes vom 14. Juni 2021 (BGBl. I S. 1802) geändert worden ist

Landesrecht

- **SächsBO**
  Sächsische Bauordnung in der Fassung der Bekanntmachung vom 11. Mai 2016 (SächsGVBl. S. 186), die zuletztdurch Artikel 1 des Gesetzes vom 1. März 2024 (SächsGVBl. S. 169) geändert worden ist.

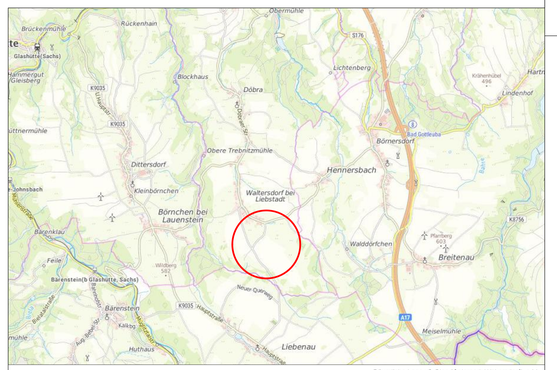

Räumliche Lage vB-Plan "Solarpark Waltersdorf", o.M.

vorhabenbezogener Bebauungsplan "Solarpark Waltersdorf"	
Planteil A - Zeichnerische Festsetzungen	
Planungsstand	Entwurf
Planfassung	19.12.2025
Stadt	Stadt Liebstadt Kirchplatz 2 01825 Liebstadt
Gemarkung	Waltersdorf
Maßstab	1 : 2.000